UNIVERSIDAD
EAFIT



Para el DNP la “asociación territorial involucra una estrecha colaboración entre dos o más instituciones o entidades, manteniendo cada una de ellas su autonomía y atendiendo, además, sus responsabilidades y derechos específicos dentro de dicha asociación” (Departamento Nacional de Planeación, 2013, p. 9).

OPORTUNIDADES: USOS Y BENEFICIOS DE LA ASOCIATIVIDAD

¿Para qué sirven?	Ejemplos	¿Quienes lo han hecho?
Ejecución de proyectos a escala y de impacto regional	Vía Terciaria, Banco regional de maquinaria	ASOCENTRO-Asociación de municipios de Sabana Centro
Coordinación de temas estratégicos	Defensa jurídica del territorio,electrificación, Fortalecimiento Institucional a ET	Asomunicipios Asociación de municipios del Catatumbo, la provincia de Ocaña y el Sur del Cesar
Ordenamiento Territorial Regional	PMOT	Áreas Metropolitanas
Prestación y regulación de servicios públicos supramunicipales regionales	Transporte, autoridades ambientales.	Áreas Metropolitanas de Valle de Aburra y Bucaramanga

UNIVERSIDAD EAFIT

DNP Nacional de Planeación

TODOS POR UN NUEVO PAÍS
PAZ EQUIDAD EDUCACIÓN

Gráfico 4. Objetivos de los esquemas asociativos según importancia brindada por los encuestados

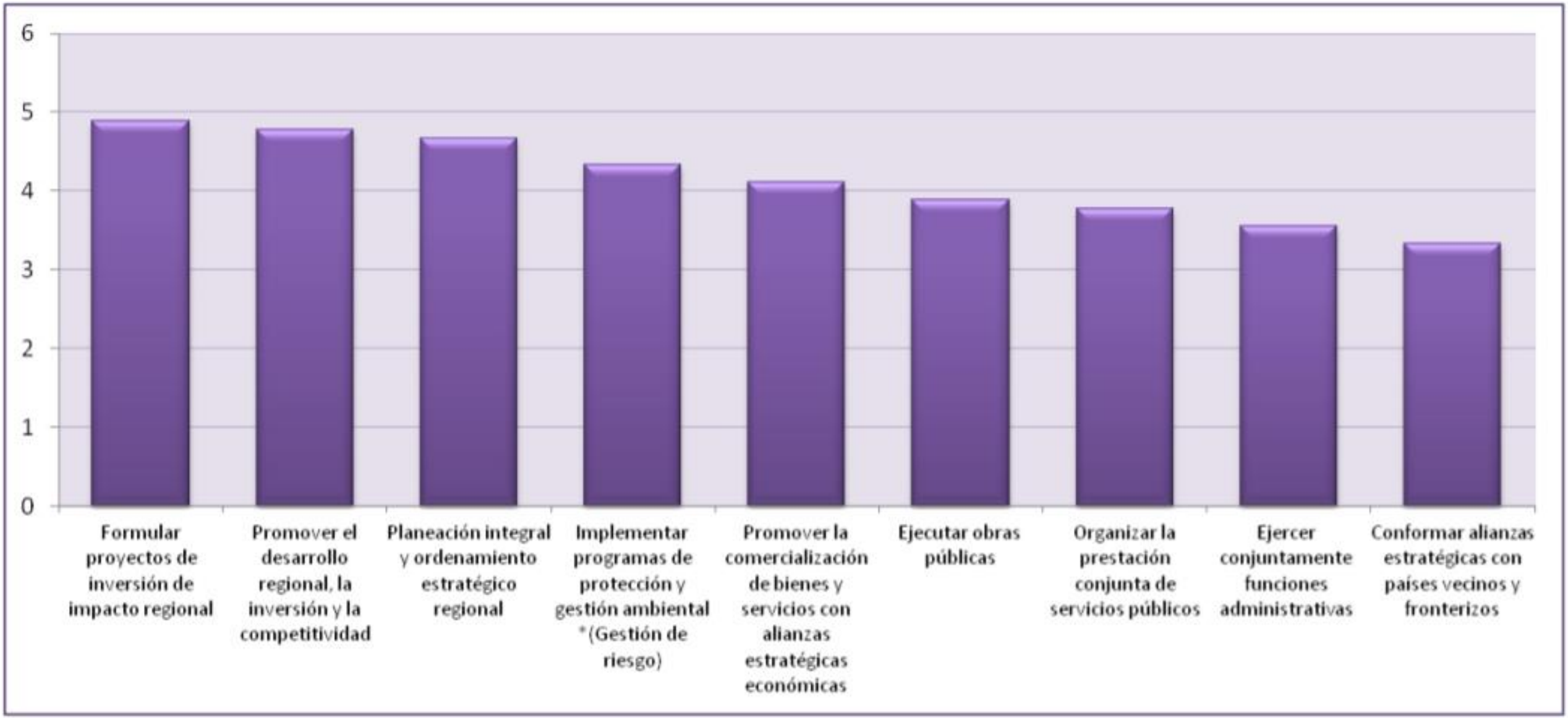

Elaboración DDTS-SODT, 2013.

UNIVERSIDAD EAFIT

Tomado de:
DNP, 2013, p.34

Objetivos de los EAT

Conformar alianzas estratégicas que impulsen el desarrollo autónomo y auto sostenible procurando un mejor nivel de vida de las comunidades

- Cumplir funciones Administrativas propias o asignadas a al ET por el nivel nacional
- Generar economías de escala
- Realizar acciones de impacto regional, ejecutar obras de interés común y cumplir funciones de planificación
- Regular actividades de tipo regional, Ambiente-Transporte
- Articular objetivos, programas, proyectos y acciones alrededor de una **visión compartida**
- Generar **sinergias y alianzas** para una mayor eficiencia y eficacia en la provisión de bienes y servicios
- Fortalecer la institucionalidad, la **gobernabilidad** y la capacidad de negociación con otros actores claves del desarrollo.

UNIVERSIDAD EAFIT

DNP Departamento Nacional de Planeación

TODOS POR UN NUEVO PAÍS

Los fines en la Ley 1625 de 2013, Ley de Áreas Metropolitanas

"La Ley de Áreas Metropolitanas aborda problemas comunes que afectan a las grandes ciudades, como los rellenos de basuras, el transporte intermunicipal, la armonización de los Planes de Ordenamiento Territorial y la integración del uso del suelo. Todo, con el fin de hacer más eficiente la gestión de sus municipios, desde el concepto de "hechos o fenómenos de carácter metropolitano". (MinInterior, 2013, p.6)

UNIVERSIDAD EAFIT

La asociatividad territorial como herramienta para la gestión del desarrollo regional

La asociatividad territorial es un principio del ordenamiento territorial que se materializa en la **unión voluntaria de dos o mas entidades territoriales** con el fin de alcanzar **objetivos comunes** para:

1. Conectar territorios y **aprovechar economías de escala** en la provisión de servicios públicos y la **concurrencia de fuentes de inversión**

2. Mejorar la **focalización de inversiones** en proyectos con mayor impacto regional y subregional

3. **Ejercer competencias** en un modelo de planificación integral conjunto

4. **Articular** objetivos, programas, proyectos y acciones alrededor de una **visión compartida de territorio**

Fuente; GEIH, DANE

Oportunidades en la práctica: Usos y beneficios comprobados

Ejecución de proyectos a escala regional

Ejemplo: Vía Terciaria, Banco regional de maquinaria (ASOCENTRO).

Coordinación de temas estratégicos

Ejemplo: Defensa jurídica del territorio, electrificación (Asomunicipios Catatumbo, Ocaña, Sur del Cesar).

Ordenamiento Territorial Regional

Ejemplo: PMOT (Áreas Metropolitanas).

Prestación y regulación de servicios públicos

Ejemplo: Transporte, autoridades ambientales (Áreas Metropolitanas de Valle de Aburra y Bucaramanga).

UNIVERSIDAD EAFIT

COMPARTIDOS: “Fenómenos que implican interconexiones territoriales y temáticas entre los municipios de la subregión, y que justamente por esto, hacen que las soluciones requeridas desborden las jurisdicciones de las autoridades de un solo municipio”

COMUNES: “Son fenómenos de los que no pueden predicarse interconexiones territoriales, pero que comparten las causas que soportan la ocurrencia común del fenómeno en toda la subregión”

LOCALIZADOS: “Se refiere a fenómenos cuya ocurrencia está delimitada territorialmente y que implican retos puntuales”

Principales problemas identificados en los esquemas asociativos

UNIVERSIDAD EAFIT



El Dilema Estructural de la **Gobernanza Territorial**

> “¿Qué mecanismos han evolucionado para resolver la autoridad fragmentada y los problemas de acción colectiva resultantes? y ¿qué sabemos sobre ellos?”
>
> (Feiock y Scholz, 2013)

Dicho de otra manera, ¿cómo pueden las autoridades locales organizarse para obtener beneficios colectivos de la coordinación de políticas ante problemas de incertidumbre y compromiso asociados a dilemas colectivos?

UNIVERSIDAD EAFIT

Protocolo de Revisión

Este proyecto implementa un protocolo de revisión sistemática inspirado en **PRISMA** (Preferred Reporting Items for Systematic Reviews and Meta-Analyses) para garantizar transparencia, replicabilidad y rigor en la revisión de literatura.

Estado del Corpus Bibliográfico	Valor
Papers incluidos	56 (de 92 identificados)
Fichas de extracción completadas	56 (100%)
Búsquedas sistemáticas	8 (1 semilla + 7 temáticas)
Líneas temáticas	7
Referencias BibTeX	56 entradas en references.bib
Última actualización	2025-05-23

Líneas Temáticas

La revisión se organiza en 7 líneas temáticas que cubren los fundamentos teóricos y la evidencia empírica del proyecto:

# Línea temática	Papers	Búsqueda
1. Cooperación intermunicipal y esquemas asociativos	27	Semilla + B1
2. Federalismo fiscal y descentralización	8	B2
3. Economía espacial y desarrollo regional	3	B3
4. Cooperación en América Latina	4	B4
5. Organismos internacionales (OECD, BM, CEPAL)	8	B5
6. Transporte rural e intermunicipal	1	B6
7. Catastro y administración de tierras	5	B7

Distribución por línea temática

Línea temática	N	Período	Tipo de evidencia principal
1. Cooperación intermunicipal	27	2005–2025	Meta-análisis, estudios empíricos, marcos teóricos
2. Federalismo fiscal y descentralización	8	1956–2025	Obras seminales, working papers
3. Economía espacial y desarrollo regional	3	1991–2009	Artículos seminales, reportes de política
4. Cooperación en América Latina	4	2019–2025	Estudios empíricos (Brasil, Europa del Este)
5. Organismos internacionales	8	2005–2025	Reportes OECD, Banco Mundial, CEPAL
6. Transporte rural e intermunicipal	1	2022	Revisión de literatura
7. Catastro y administración de tierras	5	2006–2024	Reportes BM, documentos de política.

Marcos teóricos fundamentales

Cuatro pilares teóricos sustentan el análisis del proyecto. Cada uno ilumina una dimensión diferente del problema de la consolidación territorial

[Paradigma central del proyecto]

Acción Colectiva Institucional

Base Teórica: *Institutional Collective Action (ICA) Framework* (Feiock, 2013; Kim et al., 2020).

Premisa: La fragmentación jurisdiccional genera dilemas de acción colectiva.

Mecanismo: Los gobiernos locales resuelven estos dilemas mediante mecanismos institucionales de complejidad creciente.

Federalismo Fiscal

Premisa: La descentralización puede mejorar la provisión de bienes públicos.

Condicionante: Fundamenta bajo qué condiciones específicas este modelo falla.

Nueva Geografía Económica

Premisa (NEG): Las actividades económicas tienden a concentrarse en lugares específicos.

Impacto: Explica las implicaciones críticas de esta concentración para los territorios periféricos.

Administración del Territorio

Premisa: Basado en la literatura de administración de tierras y sistemas catastrales.

Herramienta: Fundamenta el rol del catastro multipropósito como motor de desarrollo territorial.

UNIVERSIDAD EAFIT

Oportunidades y factores habilitantes

Condiciones que impulsan la cooperación intermunicipal efectiva

Economías de Escala

Municipios pequeños se benefician desproporcionadamente en residuos, transporte y tributación.

- **Suecia:** municipios <5 000 hab. cooperan **3× más** que los grandes.
- **España:** cada −10 % de población eleva la probabilidad de cooperar en **+3.2 pp**.

Presión Fiscal como Motor

Predictor más robusto de cooperación (***β = 0.15****** en meta-regresión de 154 coeficientes).

- **Países Bajos:** cooperación aumentó **+23 %** durante la crisis 2008–2012.
- **Colombia:** municipios Cat. 5–6 presentan baja generación de ingresos propios — condición ideal.

Capital Social Acumulado

La experiencia previa en cooperación es el predictor más fuerte de cooperación futura.

- **Brasil:** municipios con experiencia previa son **16× más propensos** a unirse a nuevos consorcios.
- **PAP Cartama** ilustra este principio con décadas de asociatividad informal en el suroeste antioqueño.

Marco Legal Habilitante

Colombia cuenta con un marco jurídico progresivamente más favorable:

Ley 1454	Ley 1962	Ley 1955	CONPES 3859
2011 · Creó las PAPs	2019 · Hechos Provinciales	2019 · EATs Gestores Catastrales	Catastro Multipropósito

Facilitación Departamental

Las instituciones intermedias reducen costos de transacción. En Antioquia, la alianza tripartita actúa como catalizador efectivo:

- **Gobernación de Antioquia**
- **Universidad EAFIT**
- **Proantioquia**

Provee asistencia técnica, moviliza recursos y construye capacidades sin imponer desde arriba.

UNIVERSIDAD EAFIT

Bel & Warner (2015, 2016) · Allers & de Greef (2018) · Grin & Abrucio (2022) · DNP (2019) · OECD (2019a) · Sanabria Pulido et al. (2025)

Barreras para la consolidación territorial

1. Costos de transacción altos

- El ICA Framework predice que mecanismos multipropósito como las PAPs enfrentan costos de transacción particularmente altos: negociación entre múltiples actores, monitoreo de acuerdos complejos, enforcement de compromisos

2. Capacidad institucional débil

- Los municipios de categoría 5 y 6 — que componen la mayoría de las PAPs — carecen de personal técnico especializado, sistemas de información y capacidad de gestión de proyectos

3. Desconexión de instrumentos nacionales

- La barrera principal NO es jurídica sino operativa: las PAPs están legalmente constituidas pero excluidas de los principales instrumentos de planificación y financiamiento del Estado

UNIVERSIDAD EAFIT

Barreras para la consolidación territorial

4. Cultura municipalista

Colombia presenta un “municipalismo excesivo” — una cultura política que concentra la identidad y la toma de decisiones en el nivel municipal, resistiendo la coordinación supramunicipal.

5. Ciclos electorales

Los líderes municipales cambian cada 4 años, amenazando la continuidad de compromisos provinciales de largo plazo(Bardhan, 2002).

UNIVERSIDAD EAFIT

Cuellos de Botella Operativos

Obstáculos para la consolidación de las Provincias (PAPs)

1. Sin financiamiento estable

Las PAPs dependen de aportes voluntarios de los municipios miembros y de financiamiento externo temporal. No existe fuente de ingreso dedicada ni fórmula de transferencias para el nivel provincial.

2. Brecha de capacidad técnica

Los municipios de categoría 5-6 no pueden formular proyectos de regalías (costo estimado: ~COP 100M por proyecto), implementar catastro, ni gestionar reportes financieros a escala supramunicipal.

3. Competencias confusas

Existe traslape entre funciones de la PAP, el departamento y las agencias nacionales. Ejemplo: el catastro sigue siendo primariamente función del IGAC (nacional), aunque la ley permite descentralización; las reglas de transición son ambiguas.

4. Exclusión de instrumentos de política

Las PAPs no están integradas en los principales canales de recursos del Estado colombiano: Pactos Territoriales, procesos SGR, ciclos de planificación del PGN.

5. Vacío de aprendizaje institucional

Cartama es la primera PAP formalizada; las otras 5 PAPs de Antioquia están en etapas más tempranas. No existen mecanismos sistemáticos de transferencia de conocimiento. Cada PAP reinventa el proceso.

UNIVERSIDAD EAFIT

Primer desafío: Generar reconocimiento de los EAT

DESAFÍO 1:
Falta de reconocimiento de los EAT

No están claras **las diferencias entre figuras,** ni su rol respecto a las ET

Los EAT no son objeto de financiación por el Gobierno Nacional

Experiencias valiosas desde las regiones que no se conocen ni replican

Inexistencia de lineamientos para determinar las **capacidades y** competencias actuales y potenciales

Asistencia técnica "1 a 1" que no se aprovecha ni sistematiza

ESTRATEGIAS
para superar los desafíos

Art 249 PND Registro formal de EAT/
Decreto reglamentario EAT

→

Art 249 PND registro y acceso a los OCAD
Art 250 pactos territoriales
Art 251 inversión en otras jurisdicciones y gestión catastral

→

Kit de Asociatividad territorial

→

Acompañamiento a la formulación de proyectos supramunicipales

→

PRODUCTOS
esperados

Registro único de EAT que sirva como su carta de representación, y que de cuenta de su experiencia e idoneidad para ejecutar recursos OCAD.

Decreto reglamentario EAT + registro

Kit de Asociatividad formulado: asistencia técnica sistematizada y disponible en línea y **mecanismos de evaluación y seguimiento**

Líneas claras sobre gestión de proyectos, ejecución de $ de regalías, capacidades actuales y potenciales, su rol en el marco de los pactos territoriales y catastro.

Procesos unificados de conformación**,** esquemas de sostenibilidad financiera, estructura institucional y administrativa

UNIVERSIDAD EAFIT

El futuro es de todos
DNP Departamento Nacional de Planeación

Mapa 3. Procesos asociativos municipales en la Región Caribe

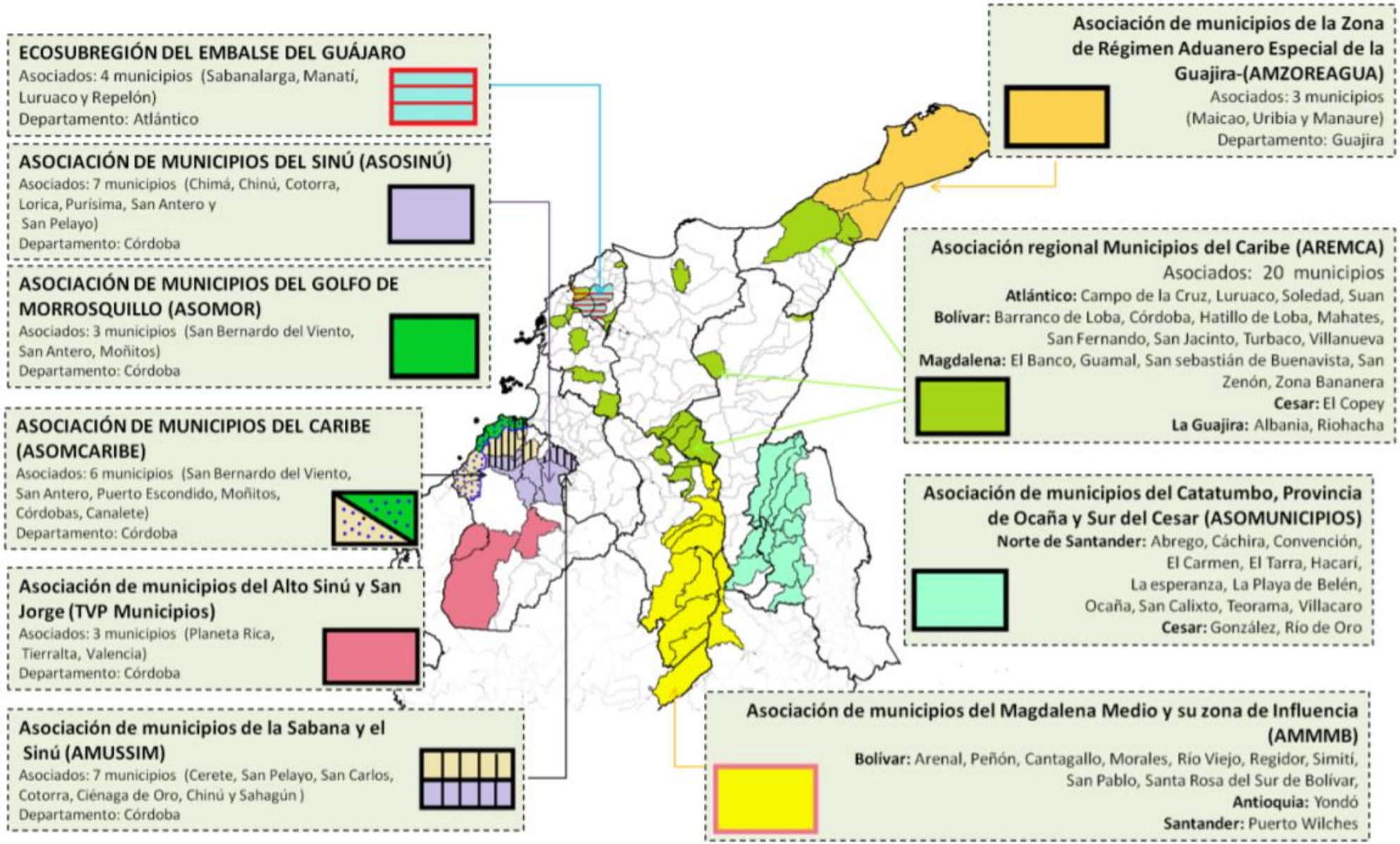

Elaboración DDTS-SODT, 2013.

Tomado de:
DNP, 2013, p.25

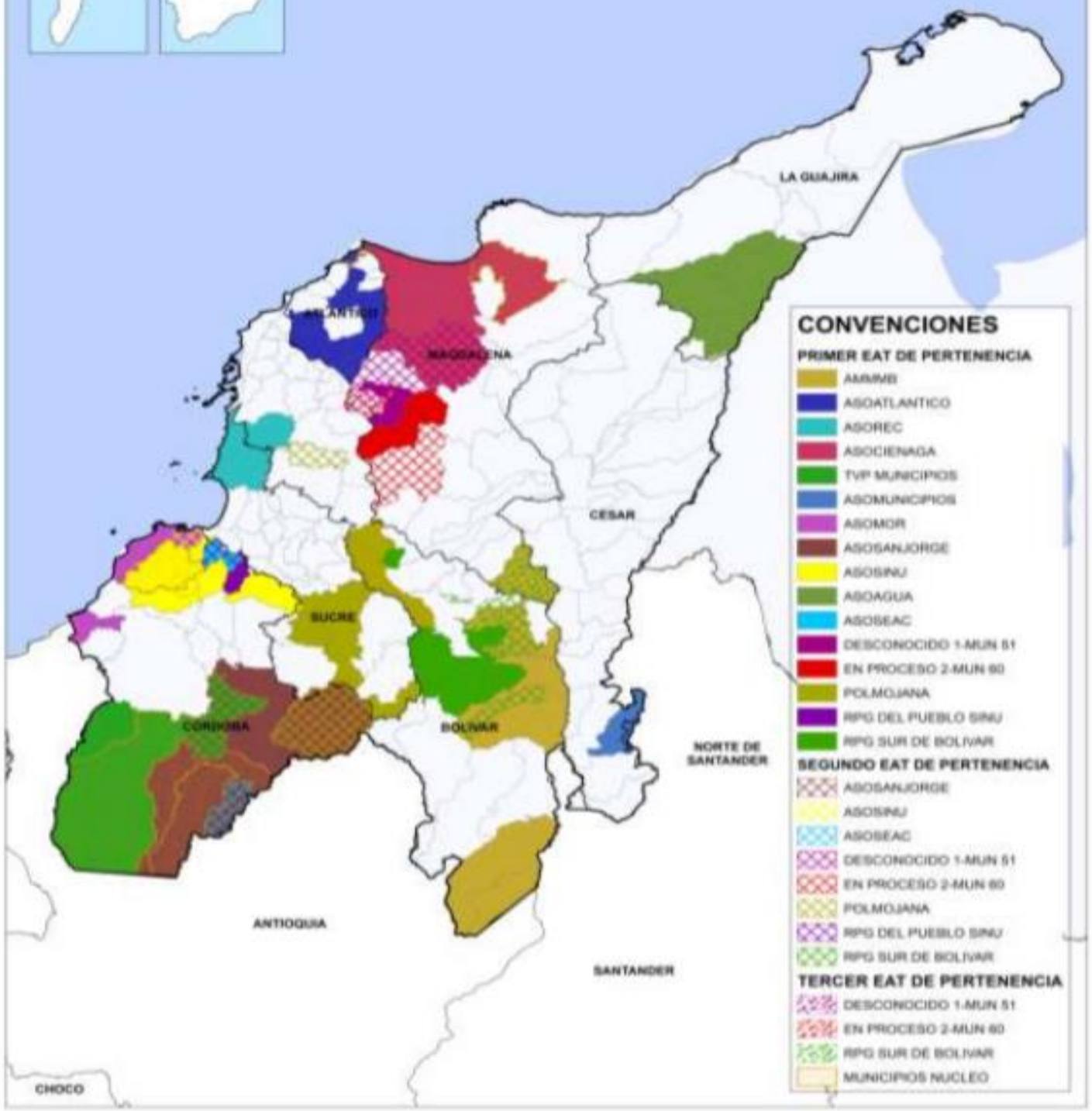

Tomado de: Economía Urbana, 2017, p.52

UNIVERSIDAD EAFIT

Mapa 5. Procesos asociativos municipales en la Región Eje Cafetero - Antioquia

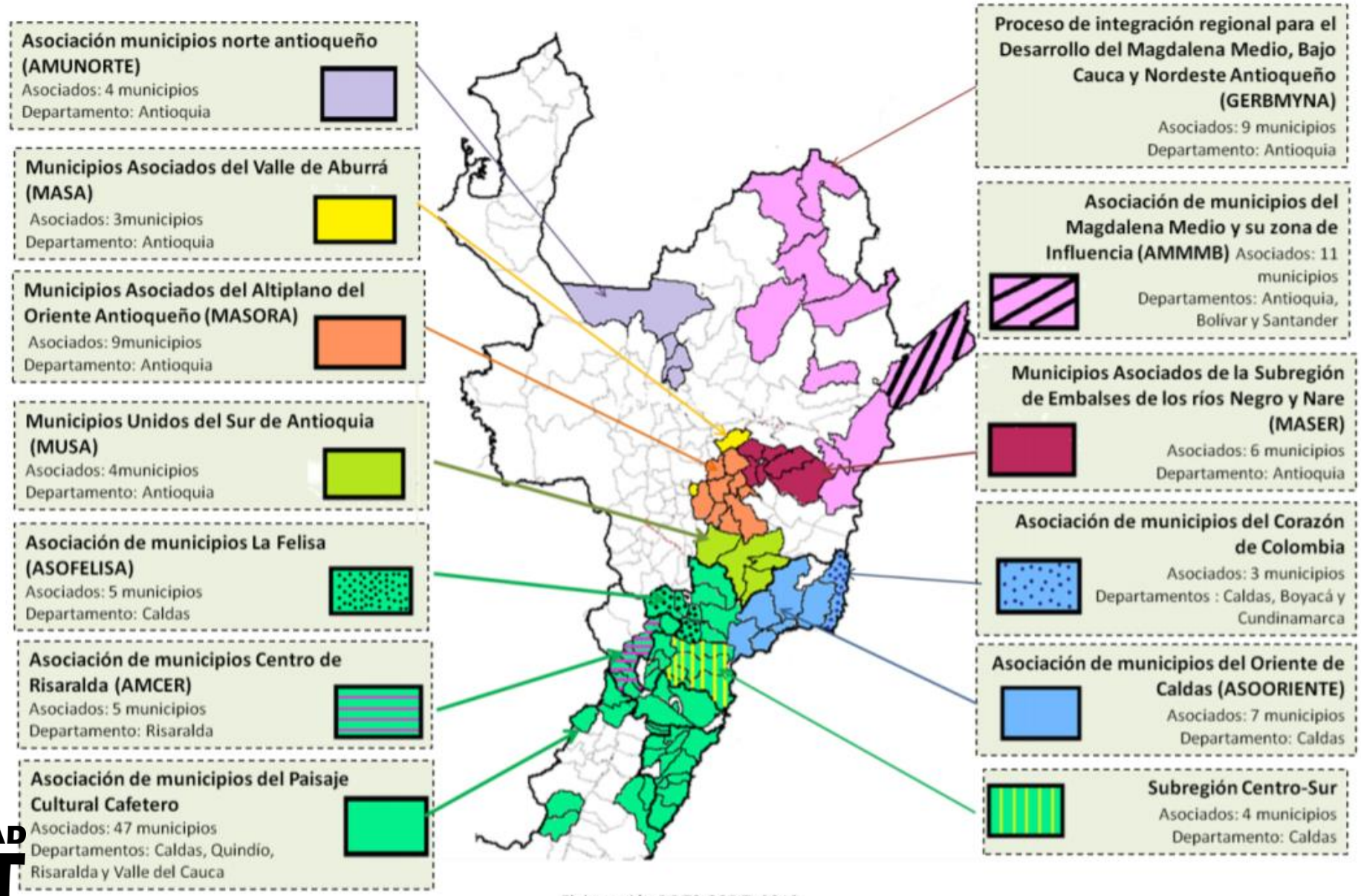

Elaboración DDTS-SODT, 2013.

Tomado de:
DNP, 2013, p.27

UNIVERSIDAD EAFIT

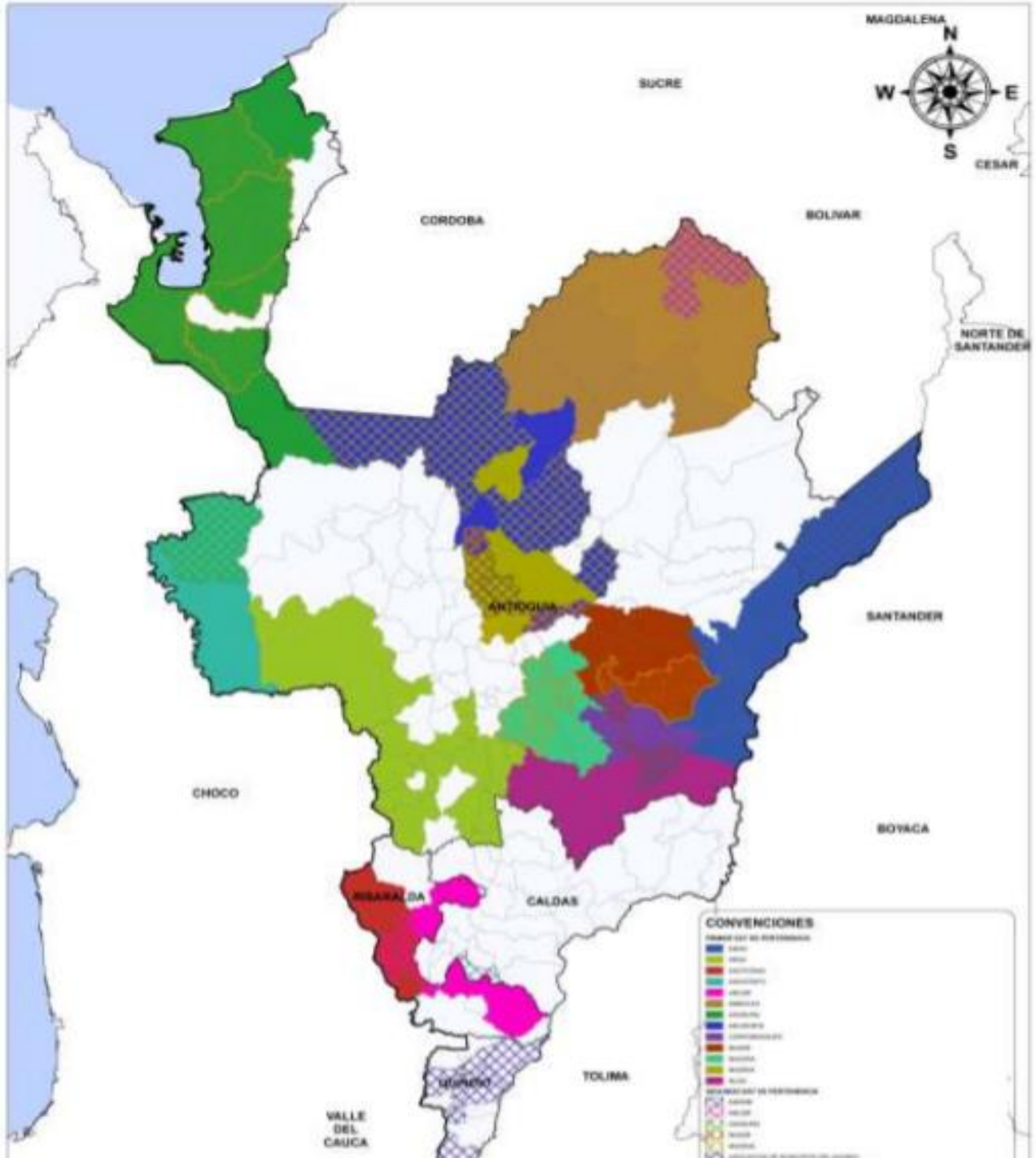

Tomado de: Economía Urbana, 2017, p.53

UNIVERSIDAD EAFIT

El papel del gobierno nacional…

DESAFÍO 2: Fortalecer las capacidades de los EAT	**ESTRATEGIAS** para superar los desafíos	**PRODUCTOS** esperados
Necesidad de fortalecer el ciclo de planeación y ejecución de **proyectos de impacto regional.**	Kit de Asociatividad territorial y asistencia técnica SGR-OCAD →	**Lineamientos del nivel intermedio** de planeación **consolidado**
Necesidad de **especializarse** y no competir con sus miembros	Misión de Descentralización-Régimen Deptal. y municipal. →	**Proyectos** formulados y ejecutados con **impacto regional**
Necesidad de **construir una visión regional y subregional acorde con los instrumentos de ordenamiento y desarrollo territorial**	Acompañamiento a la formulación de proyectos supramunicipales →	Contar con un instrumento regional que integre el desarrollo y el ordenamiento del territorio para facilitar la toma de decisiones
En el caso de las RAP: necesidad de **garantizar una mejor transición hacia las RET** a diferentes niveles.	PGOT →	Contar con **RAP fortalecidas**, **roles definidos** y condiciones claras para la creación de las en nuevas RET: capacidades, estructura institucional y administrativa, entre otros

Tomado de: DNP, 2013, p.27

UNIVERSIDAD EAFIT

El futuro es de todos

DNP Departamento Nacional de Planeación

El proyecto como estrategia de EAT "fuertes"

1. Planes provinciales

- El trabajo de hacer planes provinciales con un enfoque a hechos provinciales claros y con un criterio de gobernanza y fortalecimiento.

2. Fortalecimiento de catastro y de un fondo de financiamiento

- El paso definitivo es la transferencia de competencias catastrales (esto es totalmente novedoso) y la creación de un fondo para el financiamiento.

3. Narrativa de descentralización (EAT +Competencias)

- La narrativa de la descentralización desde abajo que complementa a la Misión de desecentralización.

UNIVERSIDAD EAFIT

Intervención con mayor potencial transformador: cumple cuatro funciones simultáneas.

Función Fiscal

Ciclo virtuoso: El recaudo se traduce en inversión local clave (salud, educación). La actualización multiplica entre **2x y 4x** el recaudo predial (DNP, 2019).

Tenencia y Equidad

Seguridad jurídica: Vital para la inversión. Vincula levantamiento físico con registro legal, con meta del **40% de títulos para mujeres**.

Planificación Territorial

Datos precisos: Evitan asentamientos en zonas de alto riesgo y optimizan la infraestructura mediante zonificación técnica alimentada por datos de POT/EOT.

Función Interjurisdiccional

Eficiencia asociativa: Modelo de las PAPs para reducir costos operativos y compartir expertos técnicos, logrando economías de escala (Ley 1955 de 2019).

Función de Planificación Territorial

Los datos catastrales alimentan los POT/EOT:

- Zonificación de uso y gestión de riesgo.
- Planificación de infraestructura.
- Protección ambiental.

Sin catastro actualizado, los planes se basan en información incompleta.

La PAP como Gestor (Ley 1955 de 2019)

Gestión del catastro municipal como una sola unidad:

- **Economías de escala:** En levantamiento y tecnología.
- **Estándares uniformes:** Valuación entre municipios adyacentes.
- **Spillovers:** Identificación de cuencas y zonas de riesgo.
- **Reducción de costos:** Comparado con operación independiente.

El papel del transporte intermunicipal

El transporte es la segunda competencia candidata a delegación provincial y un determinante crítico del desarrollo territorial.

La tendencia global es descentralizar la planificación y gestión del transporte hacia gobiernos locales (Hine & Cook, 2022; OECD, 2019a)

Impacto Multisectorial y ODS

- Vínculos con 10 de los 17 ODS.
- Inversión costo-efectiva en reducción de pobreza (Hine & Cook, 2022).
- 1,000 millones de personas viven a >2 km de vías transitables.

Efectos Documentados

- **Económicos:** Mercados y tecnología.
- **Salud:** Mortalidad materna/infantil.
- **Género:** Impacto desproporcionado.
- **Educación:** Asistencia escolar.

Gobernanza Descentralizada

La descentralización hacia gobiernos locales requiere (OECD, 2019a):

- Marcos claros para mantenimiento.
- Capacidad técnica para supervisión.
- Fondos viales dedicados (road funds).
- Participación comunitaria.

UNIVERSIDAD EAFIT

La narrativa como oportunidad

- El AL 03 de 2024 es una gran oportunidad para agendar cambios en el financiamiento de los EATs.

- Igualmente, este proyecto tiene el reto de ayudar a la gobernación a armar una narrativa que complemente a la Misión de Descentralización.

- Lo que se está haciendo es muy poderoso. Colombia ha tenido 5 olas de fortalecimiento (con pocos resultados). La gobernación de Antioquia está mostrando el camino a seguir para todo el país.

UNIVERSIDAD EAFIT